RÉPUBLIQUE FRANÇAISE
Liberté
Égalité
Fraternité

Cerema
CLIMAT & TERRITOIRES DE DEMAIN

GT CNIG ACCESSIBILITE

22 janvier 2026 à **9h30**

Ordre du jour

- Revue du dernier compte-rendu, actus diverses
- Infos de la Délégation Ministérielle à l'Accessibilité
- Gabarit CNIG Géopackage et QAccess
- Maintenance du standard CNIG Accessibilité
- Recherche de gains de productivité dans la collecte
- Points divers

Infos de la Délégation Ministérielle à l'Accessibilité

Infos de la Délégation Ministérielle à l'accessibilité

- Webinaire pour débutants "La politique des données d'accessibilité et l'information voyageurs"
  - Conçu pour tous les acteurs découvrant la politique des données d'accessibilité
  - 5 février de 9h à 10h
  - Zoom (lien https://developpement-durable-gouv-fr.zoom.us/s/99931040663?pk_content=link-7#success ID de réunion : 999 3104 0663 ; Code secret : 887516)
  - Parlez-en à vos collègues et partenaires qui s'intéressent au sujet
- Dans le cadre de la révision de l'arrêté voirie du 15 janvier 2007,
  - une réunion est prévue 5 février à 15h30 pour la partie sur les arrêts de bus et cars avec les acteurs de l'écosystème. lien https://developpement-durable-gouv-fr.zoom.us/j/93887975156 Code secret: 954576
  - une réflexion est en cours pour rapprocher la démarche PAVE de celle de la collecte des données (périmètre et standard des données)
- Arrivée d'une nouvelle personne dans l'équipe de la DMA, dédiée à l'accessibilité des transports collectifs : Aida Mortaziq. Muriel garde les données d'accessibilité et l'information voyageurs, l'accessibilité du stationnement et des transports individuels (taxis, Vtc, TPMR)
- Réorganisation de la DGITM avec une direction de la stratégie rattachée directement au DGTIM et au sein de la Direction des Mobilités routières, dans la sous direction ENT Expertise numérique et territoires, 2 bureaux dédiés à l'expertise numérique sous la responsabilité de Pierre CONVERT, l'un sur la politique des données (Jean Seng, chef de bureau) et le second sur systèmes d'information (Sophie Martin, cheffe de bureau)

Point d’Avancement du sous-groupe ERDA

Choix des profils

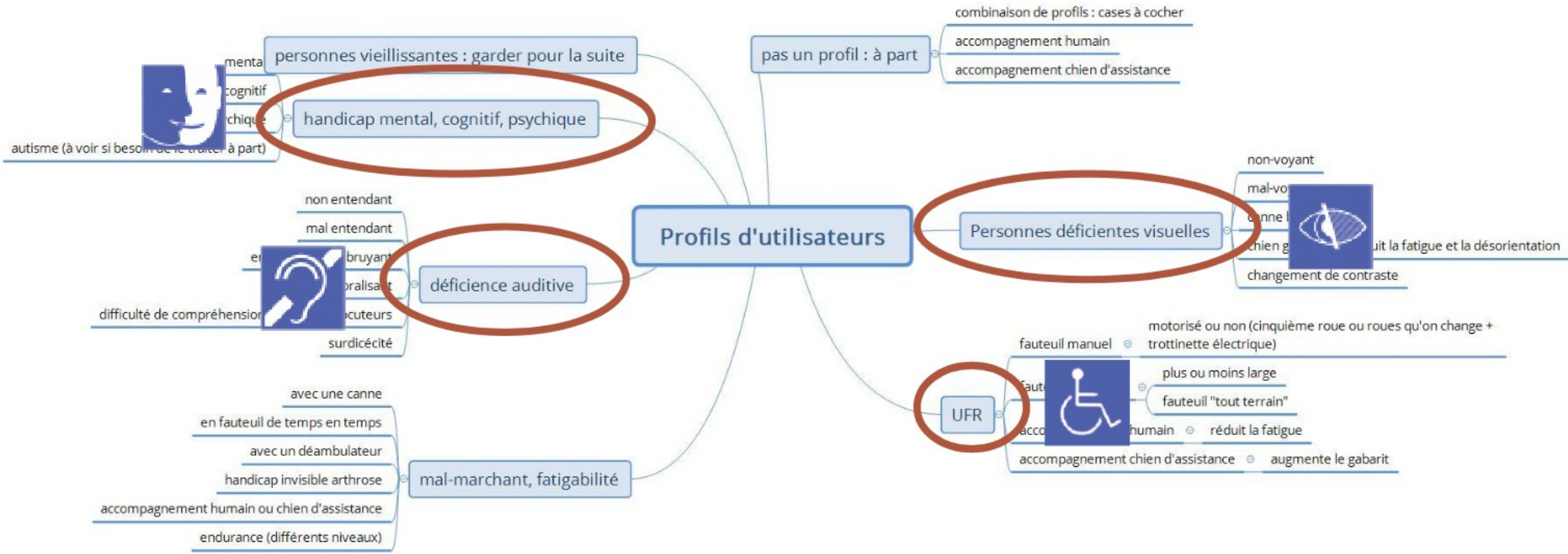

Les niveaux de qualité d’usage

- Niveaux de qualité d’usage proposés :
  - **Non déterminant** : les différentes valeurs de l’attribut n’entrent pas en compte dans le choix du parcours pour le profil en question
  - **Confortable** : valeurs toujours confortables, pour tout le monde au sein de ce profil > réalisme
  - **Neutre** : valeurs ni confortables, ni bloquantes ou dégradées
  - **Pénalisant** : utilisation « théoriquement » possible mais fortement dégradée (dangereux ou inconfortable)
  - **Bloquant** : valeurs bloquantes (« ça ne passe pas », pour personne au sein de ce profil) > pertinence

  - Avec un **système de priorités** pour faire ressortir les attributs les plus discriminants : P1 = priorité 1, P2 = priorité 2, etc.

Point d’avancement SG ERDA

- Présentations aux différents acteurs
  - le GT ERDA a présenté les résultats de deux ans de travail mené avec les associations de PSH
    - au GT7 le 20 novembre
    - aux éditeurs de calculateurs d'itinéraires le 15 décembre.
    - replay du webinaire, présentation et livrables *(également sur la page « Données d'accessibilité »)*

Gabarit CNIG
Géopackage et QAccess

Gabarit CNIG Géopackage et QAccess

- Standard CNIG Accessibilité
  - modèle de donnée relationnel, catalogue d'objets, recommandations, métadonnées, etc.
- Nécessité de lui adjoindre un format d'échange :
  - proposant une implémentation simplifiée « à plat » commune à tous les utilisateurs
  - offre un format d'import dans les outils SIG
  - rationalise les outils de collecte & visualisation avec un format unique
  - constitue le point d'entrée de la chaîne de conversion CNIG vers NeTEx
- Choix du format standard Géopackage
  - géopackage est un format standard de l'OGC
  - constituant un « format passerelle » entre les logiciels SIG

Avantages respectifs des gpkg CNIG et QAccess

Géopackage CNIG

- solution open-source
- hébergée, documentée et maintenue par le GT Accessibilité => Label CNIG
- basé sur un script SQL (ré)exécutable
- maintenance évolutive à faible coût
- synchronisé aux évolutions du standard

Géopackage QAccess + QAcess

- solution open-source
- utilisation poussée du format géopackage
- implémentation non relationnelle du modèle de données => utilisation simplifiée
- admet des extensions au standard CNIG
- format natif de QAccess :
  - utilisable sous QGIS au bureau et avec Qfield sur le terrain
  - visualisation cartographique
  - analyses de l'accessibilité du territoire

Peut-on développer un géopackage unique cumulant les avantages des deux ?

Proposition d’unification des deux géopackages :

- Le format geopackage QAccess
  - sera codé (script SQL) et remplacera le gabarit actuel pour devenir le format d’échange du standard CNIG Accessibilité => unique « format CNIG Accessibilité »
  - script SQL hébergé sur le Github du CNIG et maintenu par le GT CNIG Accessibilité
  - maintenance évolutive synchronisée à celle du standard
- La solution QGIS QAccess
  - projet QGIS facilitant la collecte, la visualisation et les analyses sur l’accessibilité
  - importe les données au format CNIG Accessibilité
  - solution mise à disposition prête à l’emploi pour les utilisateurs
  - maintenue par Someware et hébergée sur sa plateforme

Un format d’échange unique, potentiellement point d’entrée de la conversion vers NeTEx

Maintenance évolutive du géostandard

Maintenance évolutive du Standard Accessibilité

- Version publiée : Standard CNIG Accessibilité v2025-03
  - La Version courante du projet de révision est le Standard Accessibilité v2026-01
  - Suivi des évolutions : paragraphe dédié au sein du standard + tableur de suivi des évos :

Date	Version N-1	Version	Page	nature	Evolution
21/10/25	v2025-03	projet	§3.3.2	amélioration	TRONCON.pente prend la valeur conventionnelle 8888 ie 'sans objet' lorsque le tronçon supporte un escalier
02/09/25	v2025-03	projet	§3.5	amélioration	ajout des attributs optionnels ESCALIER.regularite et ESCALIER.rampeInterne
28/08/25	v2025-03	projet	§3.3.17	correction	idStationnment est renommé idStationnmentPmr
19/08/25	v2025-03	projet	§3.5	correction	corrections dans le classement alphabétique des listes énumérées
20/06/25	v2025-03	projet	§3.3.16	correction	QUAI.etatRevetement : liste etat_revetement et pas liste etat (et idem pour STATIONNEMENT_PMR)
20/06/25	v2025-03	projet	§3.3.13	correction	ELEVATEUR.typeOuverture : valeur NC non autorisée
17/06/25	v2025-03	projet	§3.5	amélioration	révision des valeurs de la liste « état », cf issue #62
17/06/25	v2025-03	projet	§3.3.12	amélioration	nouvel attribut ASCENSEUR.opaciteParois, cf issue #60
06/06/25	v2025-03	projet	§3.3.3	correction	pas de valeur vide par défaut pour NOEUD.abaissePente
14/03/2025 - DIFFUSION DU STANDARD CNIG Accessibilité v2021-10 rev2025-03					

Maintenance évolutive du Standard

- Dernières évolutions dans les issues du Github :

- remplacer rampe = 03 par sa valeur 'absence' dans le standard Traité
  #76 · YohanGIBERT opened 5 days ago
- Erreur lors de l'enregistrement d'un noeud dans le gpkg CNIG Accessiblité avec QGIS Traité
  #75 · nicolas-demagny opened on Nov 24, 2025
- corrections listes de valeurs dans standard pdf Traité
  #74 · YohanGIBERT opened on Aug 19, 2025
- Proposition ajout type 'accotement' pour les tronçons de cheminement En cours
  #73 · YohanGIBERT opened on Jul 15, 2025
- Gabarit CNIG Accessibilité au format géopackage Traité
  #72 · GT-CNIG-DDU opened on Jul 11, 2025
- Largeur du cheminement sur des chaussées sans trottoir ou partagées avec les voitures Traité
  #71 · antoine-tesson opened on Jul 3, 2025
- Signalétique En cours
  #70 · Lenoxaic opened on Jul 2, 2025
- Nouveaux attributs pour la classe ESCALIER Traité
  #69 · GT-CNIG-DDU opened on Jun 17, 2025
- TRONCON.pente dans le cas d'un escalier Traité
  #68 · Marion-Torterotot opened on Jun 6, 2025
- RAMPE.distPalierRepos Traité
  #67 · Marion-Torterotot opened on Jun 6, 2025
- Classes d'objets portant l'attribut typesol Traité
  #66 · antoine-tesson opened on Apr 17, 2025
- Collecte obligatoire de la présence de repèreLineaire ? Traité
  #64 · TuThoThai opened on Mar 14, 2025

Rappel

Contribuer via les « Issues » du Github

- Créer un compte Github
- Cliquer sur Watch pour s'abonner aux issues
- Et choisir All activity pour recevoir un mail à chaque contribution

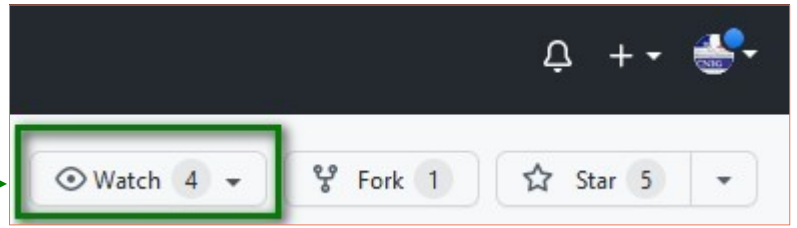

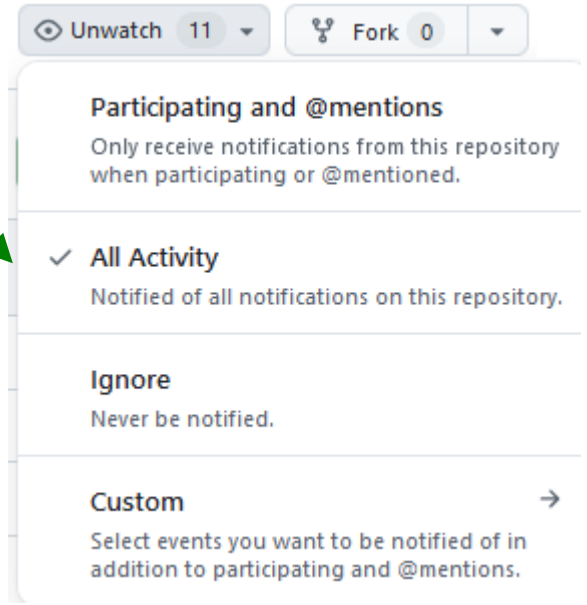

Recherche de gains de productivité dans la collecte

Collecte des données d'accessibilité

Constats et propositions autour du standard CNIG et des PAVE

Atipy
Conception universelle et +

Contexte général

Un cadre réglementaire clair (ou pas)…

- Loi du 11 février 2005 (concerne la voirie)
- Loi LOM (concerne la mobilité)
- Pas de coordination si pas de communication inter service

…mais une mise en œuvre très limitée

- Peu de collectivités engagées
- Peu de relevés réellement réalisés

Identification des causes

Trois freins principaux :

- Contraintes budgétaires
- Manque de clarté réglementaire
- Coût et complexité de la collecte

Difficultés autour du relevé CNIG et des PAVE

Mobilisation difficile des collectivités

Faible nombre d'appels d'offres :

- 5 à 6 par an seulement (et encore…)
- alors qu'il devrait y en avoir plusieurs dizaines

Relevés souvent repoussés ou abandonnés

Le précédent des Ad'AP

- Cadre clair fixé par l'État
- Objectifs précis
- Sanctions applicables

Résultat :

- Mobilisation réelle des collectivités
- Moyens financiers trouvés
- Effets positifs sur l'accessibilité du bâti

Notion à retenir

→ Le frein n'est pas uniquement financier :
volonté politique, clarté réglementaire et sanctions sont déterminantes

Synthèse

Causes

- CNIG ne couvre pas tout le champ réglementaire
- PAVE présente aussi des limites
- Difficulté à expliquer la cohérence CNIG / PAVE / NeTEx
- Absence de sanctions réglementaires
- Contexte financier tendu

→

Conséquences

- Hésitation à se lancer
- Hétérogénéité des appels d'offres
- Cahiers des charges très variables

Propositions

Modifier la philosophie des attributs obligatoires

→ Philosophie actuelle : pas de donnée interprétée : uniquement des mesures

- CNIG impose le relevé d'attributs partout
- Même en l'absence de problème

Une utilité discutable

- Un calculateur d'itinéraire peut interpréter :

absence d'attribut = absence de difficulté

- Saisie systématique = donnée inutile
- Peu de valeur ajoutée pour l'usager final

Propositions d'évolution

1. Alléger l'exigence de saisie

- Pas de relevé d'attribut si aucune difficulté
- Référence des champs du relevé : arrêté du 15 janvier 2007 → et mise à jour

2. Introduire un attribut obligatoire de traçabilité

- Champ "date de contrôle" pour chaque objet (y/c les objets conformes)

Bénéfices attendus

- Réduction du temps et du coût de collecte
- Standard plus lisible
- Meilleure qualité des données
- Meilleure sobriété écologique (jeu de données unique)
- Meilleure acceptabilité par les collectivités
- Optimisation de la mise à jour

MERCI DE VOTRE ATTENTION

arnauld.gallais@cerema.fr

RÉPUBLIQUE FRANÇAISE
Liberté
Égalité
Fraternité

Cerema
CLIMAT & TERRITOIRES DE DEMAIN